JMA extreme hot days (>=35C) - 2016-2025

Coverage

- Stations in catalog: **1678**
- Stations with at least one parsed hot-day value in window: **941**

National annual trend

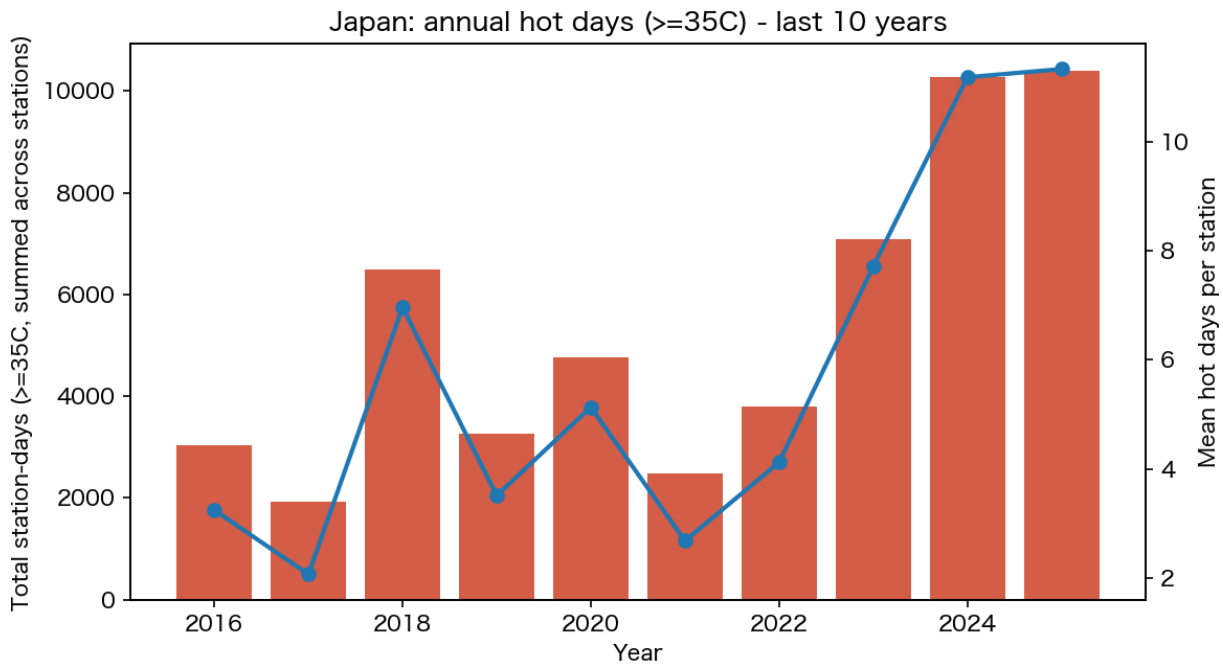

Figure 1: national trend

year	stations_reporting	total_station_days	mean_per_station	median_per_station
2016.00	933.00	3027.00	3.24	0.00
2017.00	934.00	1930.00	2.07	0.00
2018.00	932.00	6487.00	6.96	2.00
2019.00	931.00	3267.00	3.51	1.00
2020.00	930.00	4772.00	5.13	2.00
2021.00	927.00	2484.00	2.68	1.00
2022.00	920.00	3790.00	4.12	1.00
2023.00	919.00	7084.00	7.71	3.00
2024.00	919.00	10273.00	11.18	3.00
2025.00	919.00	10411.00	11.33	5.00

Top 25 hottest stations (10-year total)

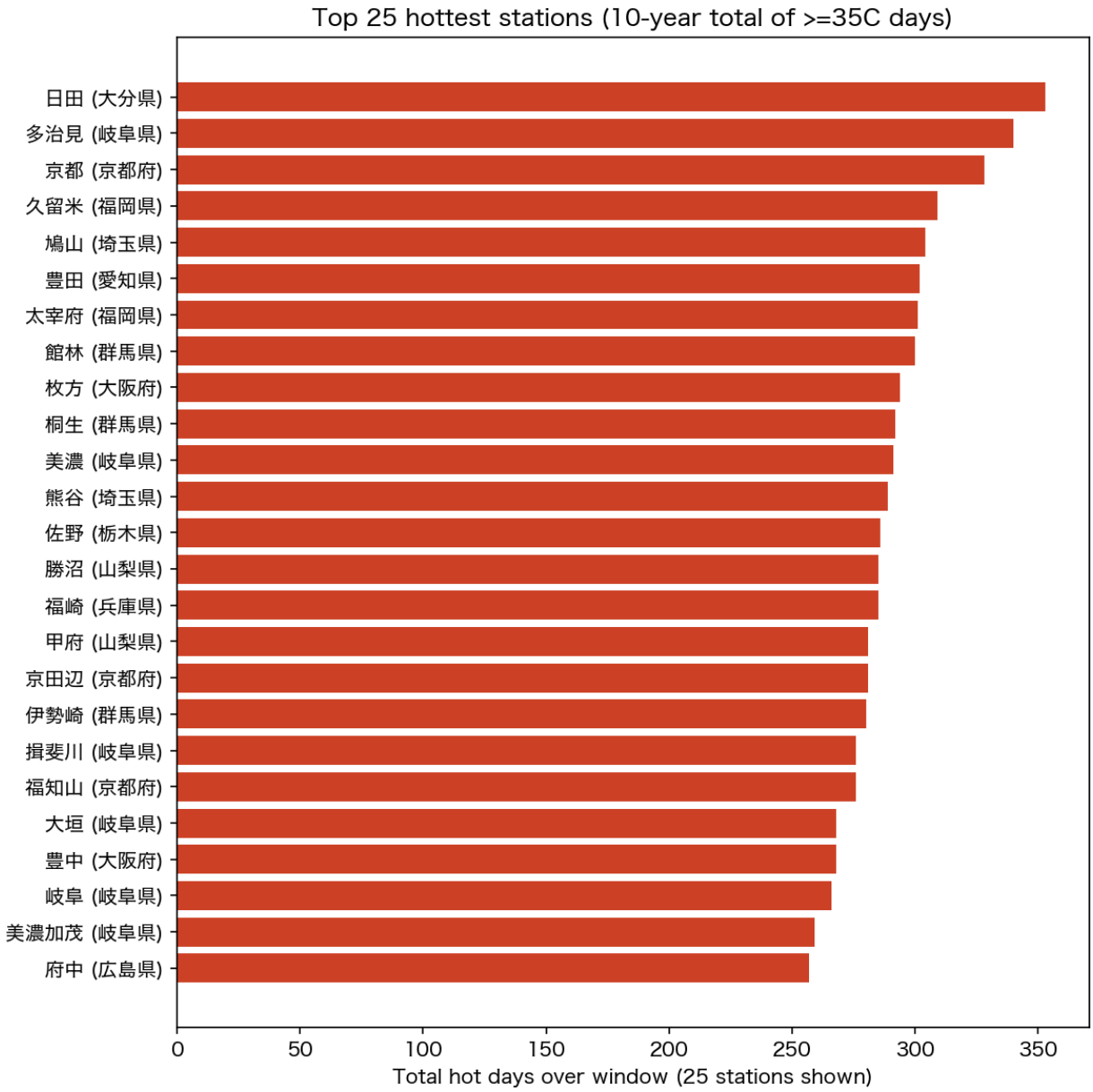

Figure 2: top stations

name	pref_name	kind	total_hot_days	mean_hot_days	max_hot_days	years_with_data
日田	大分県	s	353.00	35.30	62.00	10
多治見	岐阜県	a	340.00	34.00	59.00	10
京都	京都府	s	328.00	32.80	61.00	10
久留米	福岡県	a	309.00	30.90	54.00	10
鳩山	埼玉県	a	304.00	30.40	51.00	10
豊田	愛知県	a	302.00	30.20	57.00	10
太宰府	福岡県	a	301.00	30.10	62.00	10
館林	群馬県	a	300.00	30.00	54.00	10
枚方	大阪府	a	294.00	29.40	51.00	10
桐生	群馬県	a	292.00	29.20	58.00	10
美濃	岐阜県	a	291.00	29.10	57.00	10
熊谷	埼玉県	s	289.00	28.90	53.00	10
佐野	栃木県	a	286.00	28.60	49.00	10
勝沼	山梨県	a	285.00	28.50	50.00	10
福崎	兵庫県	a	285.00	28.50	56.00	10
甲府	山梨県	s	281.00	28.10	59.00	10
京田辺	京都府	a	281.00	28.10	60.00	10
伊勢崎	群馬県	a	280.00	28.00	51.00	10
揖斐川	岐阜県	a	276.00	27.60	53.00	10
福知山	京都府	a	276.00	27.60	58.00	10
大垣	岐阜県	a	268.00	26.80	58.00	10
豊中	大阪府	a	268.00	26.80	47.00	10
岐阜	岐阜県	s	266.00	26.60	51.00	10
美濃加茂	岐阜県	a	259.00	25.90	51.00	10
府中	広島県	a	257.00	25.70	57.00	10

Prefecture-level summary

prec_no	pref_name	total_hot_days	mean_hot_days_per_station	max_hot_days	station_years	station_year_obs
52	岐阜県	3006.00	13.07	59.00	230	
63	兵庫県	2231.00	11.15	56.00	200	
82	福岡県	2168.00	15.49	62.00	140	
86	熊本県	2150.00	11.81	53.00	182	
43	埼玉県	1835.00	22.94	53.00	80	
66	岡山県	1816.00	11.35	56.00	160	
67	広島県	1770.00	9.32	57.00	190	

prec_no	pref_name	total_hot_days	mean_hot_days_per_station_year	max_station_year	station_year_obs
42	群馬県	1630.00	12.54	58.00	130
61	京都府	1571.00	19.64	61.00	80
51	愛知県	1553.00	12.94	57.00	120
54	新潟県	1462.00	5.13	37.00	285
40	茨城県	1455.00	9.97	51.00	146
62	大阪府	1431.00	15.90	51.00	90
83	大分県	1357.00	9.05	62.00	150
53	三重県	1268.00	10.57	48.00	120
48	長野県	1257.00	4.18	42.00	301
81	山口県	1243.00	7.77	50.00	160
36	福島県	1220.00	3.91	34.00	312
49	山梨県	1191.00	10.83	59.00	110
68	島根県	1188.00	6.25	47.00	190
73	愛媛県	1128.00	7.52	36.00	150
72	香川県	1092.00	15.60	54.00	70
88	鹿児島県	1030.00	3.12	40.00	330
57	福井県	1030.00	10.30	43.00	100
41	栃木県	1023.00	7.26	49.00	141
87	宮崎県	1003.00	5.87	42.00	171
44	東京都	979.00	5.44	48.00	180
45	千葉県	978.00	6.52	40.00	150
69	鳥取県	927.00	9.27	39.00	100
50	静岡県	898.00	4.63	41.00	194
60	滋賀県	898.00	9.98	47.00	90
74	高知県	869.00	5.43	50.00	160
85	佐賀県	861.00	14.35	47.00	60
35	山形県	858.00	3.90	28.00	220
84	長崎県	769.00	4.01	50.00	192
55	富山県	769.00	7.69	37.00	100
65	和歌山県	729.00	6.08	45.00	120
64	奈良県	696.00	11.60	51.00	60
32	秋田県	657.00	2.53	26.00	260
33	岩手県	637.00	1.81	21.00	352
71	徳島県	591.00	7.30	49.00	81
56	石川県	525.00	4.77	27.00	110
34	宮城県	490.00	2.36	17.00	208
46	神奈川県	290.00	5.80	28.00	50
17	網走・北見・紋別地方	228.00	1.04	9.00	220
20	十勝地方	214.00	1.13	7.00	190
31	青森県	166.00	0.72	16.00	230
12	上川地方	135.00	0.59	10.00	230
91	沖縄県	97.00	0.37	8.00	265
15	空知地方	56.00	0.54	6.00	104
14	石狩地方	30.00	0.30	3.00	100

prec_no	pref_name	total_hot_days	mean_hot_days_per_station	max_station_year	station_year_obs
13	留萌地方	18.00	0.20	10.00	90
19	釧路地方	16.00	0.13	2.00	120
18	根室地方	15.00	0.17	2.00	90
22	日高地方	9.00	0.11	3.00	80
11	宗谷地方	6.00	0.05	3.00	130
16	後志地方	4.00	0.04	1.00	110
24	檜山地方	1.00	0.02	1.00	60
23	渡島地方	1.00	0.01	1.00	100
21	胆振地方	0.00	0.00	0.00	110
99	南極	0.00	0.00	0.00	10

Notes

- Source: 気象庁 過去の気象データ (https://www.data.jma.go.jp/obd/stats/etrn/).
- ‘猛暑日’is JMA’s official term for a day with daily maximum temperature >= 35 degC.
- AMeDAS-only stations and stations newly installed within the window may have shorter coverage; see `years_with_data` per station.
- Values flagged with ‘)’or similar in JMA tables indicate incomplete monthly aggregation; they are kept as-is in this dataset with the original flag preserved in the `flag` column. ## 猛暑日ゼロの観測地点（2016〜2025 年）

10 年間を通じて一度も猛暑日（最高気温 35°C 以上）を記録しなかった観測地点は、データのある 1,321 地点中 **153 地点**（11.6%）あった。

カテゴリ別内訳

カテゴリ	地点数	代表的な地点
北海道（沿岸・道東）	73	稚内、釧路、根室、室蘭、苫小牧、えりも岬
沿海・離島	29	勝浦（千葉）、宮古島（沖縄）、父島（東京）、室戸岬（高知）
東北（高地・内陸寒冷地）	24	酸ケ湯（青森）、薮川（岩手）、桧枝岐（福島）
高原・山岳	24	富士山（静岡・山梨）、軽井沢（長野）、草津（群馬）、阿蘇山（熊本）
南極	1	昭和基地

主な分析

北海道（73 件）が最多。道央〜道東のオホーツク海・太平洋側は夏の冷涼な海霧（やませ）の影響を受けるため、真夏でも 35°C に達することがほとんどない。胆振地方・釧路地方が丸ごと 0 件。

沿海・離島（29 件）の内訳は多様。- 沖縄の離島（宮古島・南大東島など）は南国でありながら猛暑日ゼロ。最高気温が 33〜34°C 止まりで海洋性気候が気温上昇を抑制する。- 千葉・勝浦は

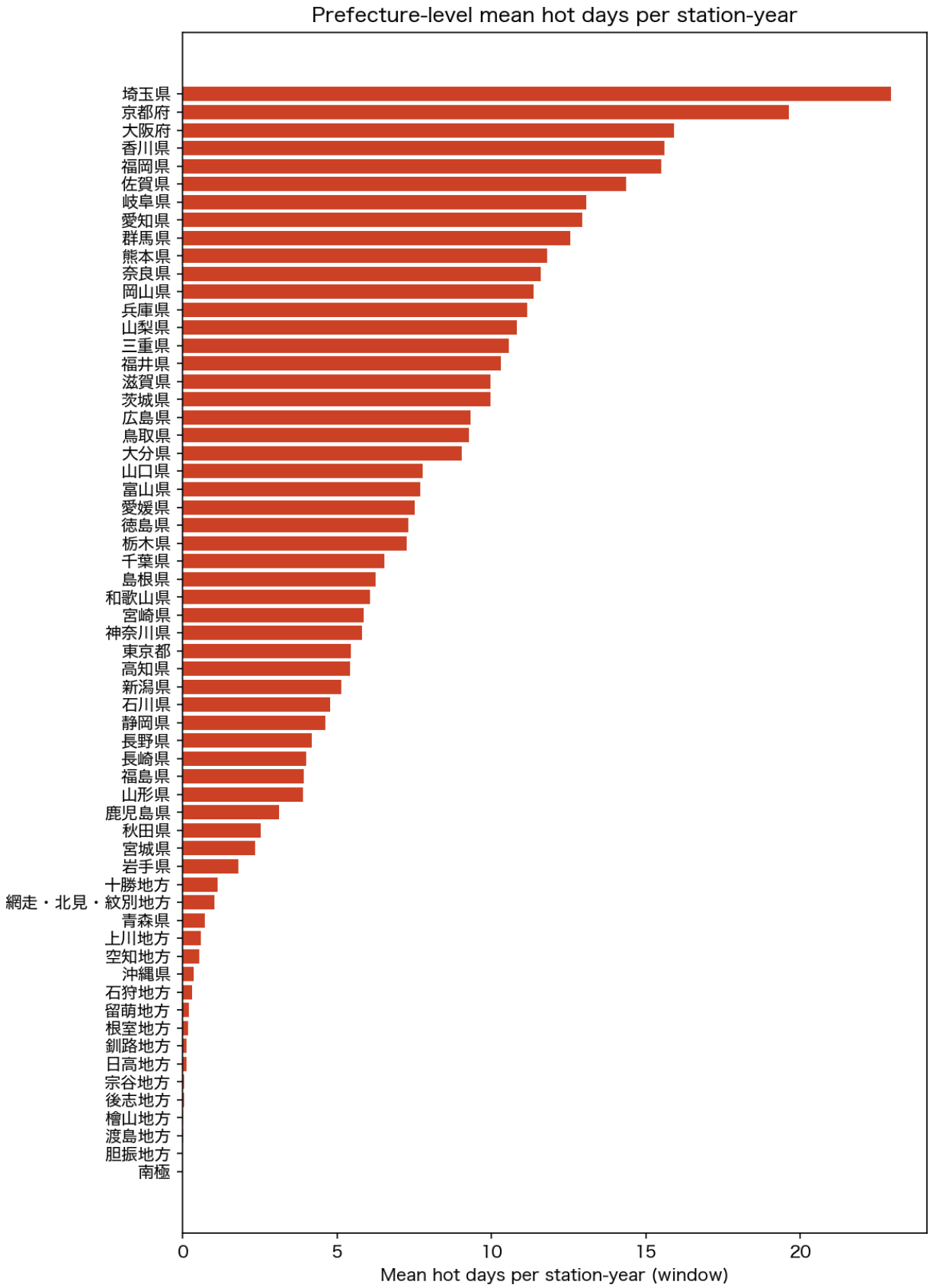

Figure 3: prefecture summary

「避暑地」として知られ、南東海風と太平洋の冷水が 35°C 超えを防ぐ。- 室戸岬（高知）・石廊崎（静岡）など岬の観測点も同様。

高原・山岳（24 件）は標高が決定的。軽井沢（約 950m）・野辺山（約 1,350m）・菅平（約 1,340m）・草津（約 1,220m）はリゾート避暑地として名高く、高地のため気温が 35°C に届かない。富士山（3,776m）は論外として、奥日光（約 1,272m）・那須高原・阿蘇山頂も同様。

東北（24 件）の多くは標高の高い山間部や下北半島〜津軽海峡沿いの地点。酸ケ湯（青森）は豪雪地帯としても知られ、夏も冷涼。

猛暑日ゼロ地点の全リスト

地点名	所在	種別	観測年数
昭和	南極	有人	10
富士山	山梨県／静岡県	有人	10
軽井沢	長野県	有人	10
稚内	宗谷地方	有人	10
北見枝幸	宗谷地方	有人	10
根室	根室地方	有人	10
釧路	釧路地方	有人	10
室蘭	胆振地方	有人	10
苫小牧	胆振地方	有人	10
浦河	日高地方	有人	10
羽幌	留萌地方	有人	10
倶知安	後志地方	有人	10
寿都	後志地方	有人	10
江差	檜山地方	有人	10
奥日光（日光）	栃木県	有人	10
勝浦	千葉県	有人	10
三宅島	東京都	有人	10
南鳥島	東京都	有人	10
父島	東京都	有人	10
石廊崎	静岡県	有人	10
宮古島	沖縄県	有人	10
南大東（南大東島）	沖縄県	有人	10
室戸岬	高知県	有人	10
平戸	長崎県	有人	10
雲仙岳	長崎県	有人	10
沖永良部	鹿児島県	有人	10
阿蘇山	熊本県	有人	2
酸ケ湯	青森県	AMeDAS	10
菅平	長野県	AMeDAS	10
野辺山	長野県	AMeDAS	10
草津	群馬県	AMeDAS	10
えりも岬	日高地方	AMeDAS	10
宗谷岬	宗谷地方	AMeDAS	10
薮川	岩手県	AMeDAS	10
桧枝岐	福島県	AMeDAS	10

地点名	所在	種別	観測年数
占冠	上川地方	AMeDAS	10
朱鞠内	上川地方	AMeDAS	10
ぬかびら源泉郷	十勝地方	AMeDAS	10
支笏湖畔	石狩地方	AMeDAS	10
高野山	和歌山県	AMeDAS	10
生駒山	大阪府	AMeDAS	10
白馬	長野県	AMeDAS	10
開田高原	長野県	AMeDAS	10
(他 118 地点)	北海道・東北・離島ほか	AMeDAS	—